B2 CONTENIMENTO DEL CONSUMO DI SUOLO: MIGLIORAMENTO DEI PARAMETRI DI QUALITÀ AMBIENTALE

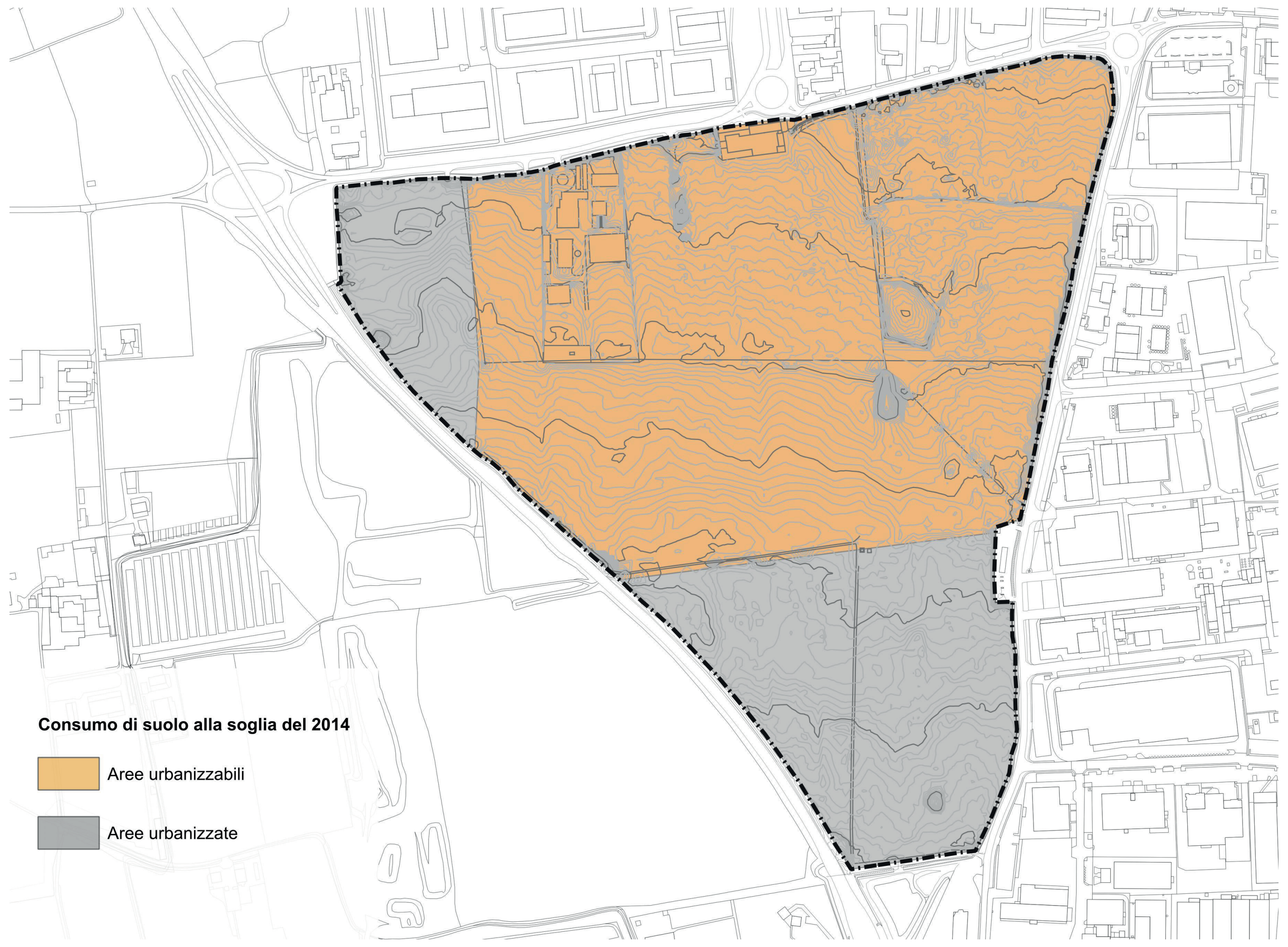
Consumo di suolo alla soglia del 2014
Aree urbanizzabili
Aree urbanizzate

RILEVARE LE TRASFORMAZIONI GIÀ ATTUATE, PRESERVARE IL TERRITORIO E RESTITUIRE AREE ALLA NATURALITÀ

Il suolo è una risorsa non rinnovabile e rappresenta un bene comune di cruciale importanza per il mantenimento dell'equilibrio ambientale e la tutela della salute.
Inoltre, svolge un ruolo essenziale nella conservazione degli ecosistemi naturali e nella prevenzione del dissesto idrogeologico.
La sua preservazione è fondamentale per garantire la stabilità ecologica e la sicurezza alimentare delle generazioni presenti e future.
In un'ottica futura, è auspicabile che si avvii un'inversione di tendenza che riporti il territorio al centro dei progetti di sviluppo sostenibile.
La pianificazione territoriale deve quindi tenere in considerazione non solo le qualità intrinseche ed estrinseche del suolo, ma anche le sue differenti vocazioni, così da valorizzarne ogni potenzialità.
Oltre agli aspetti produttivi, è necessario integrare gli elementi di qualità agricola e paesaggistica, riconoscendo il valore estetico e culturale del paesaggio rurale.
In questo scenario, una gestione consapevole del suolo diventa una priorità, garantendo un equilibrio tra sviluppo economico, rispetto dell'ambiente e salvaguardia delle risorse naturali per le generazioni future.

DATI TERRITORIALI - CONSUMO DI SUOLO

AMBITO URBANISTICO	SOGLIA 2014 (mq)	SOGLIA PROGETTO (mq)	Differenza (mq)
AREE URBANIZZATE	131.463	68.477	**-62.986**
AREE URBANIZZABILI	306.174	189.683	**-116.491**
SUOLO LIBERO	0	179.477	**179.477**
TOTALE AMBITO DI INTERVENTO	437.637	437.637	0

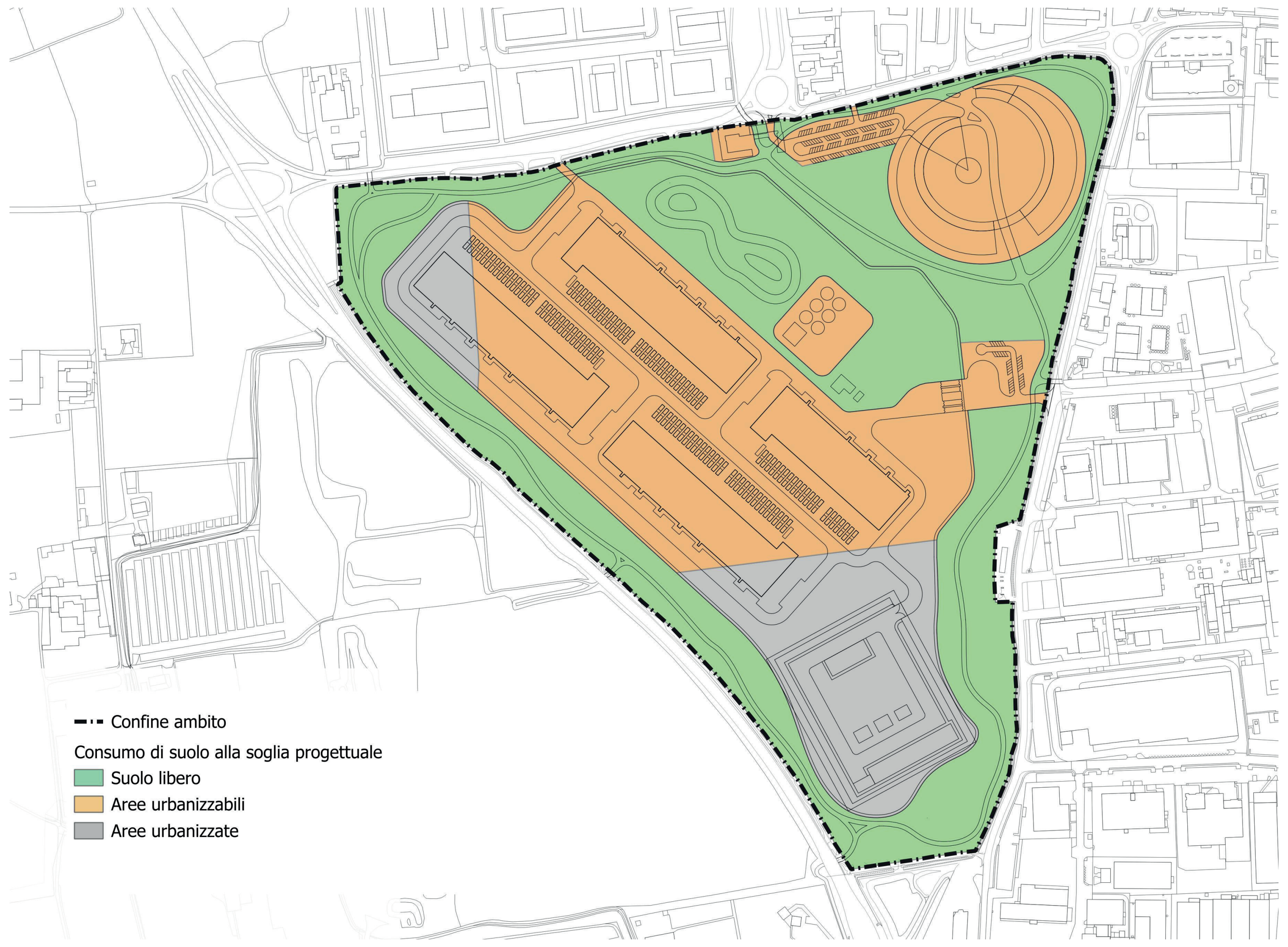
Confine ambito
Consumo di suolo alla soglia progettuale
Suolo libero
Aree urbanizzabili
Aree urbanizzate

DATI TERRITORIALI ALLA SOGLIA DEL 2014

		(mq)	SOMMA (mq)	%
Sito contaminato oggetto di bonifica regionale	AREE CRITICHE	19.911	138.754	31,71%
Sito oggetto di escavazione e successivo riempimento con rifiuti solidi urbani		16.764		
Sito oggetto di escavazione e successivo riempimento con materiale inerte		102.079		
Sito interessato da cava di prestito e successivo riempimento	AREE GIA' UTILIZZATE	58.036	113.376	25,91%
Aree dismesse dall'aereoporto militare		38.916		
Area edificata e dismessa in fase di avanzato degrado		3.364		
Aree produttive florovivaistiche e residenziali		13.060		
Aree agricole destinate a sviluppo immobiliare		185.507	185.507	42,39%
TOTALE AMBITO DI INTERVENTO		437.637	437.637	100,00%

UN TERRITORIO FERITO: TRACCE DI UN PASSATO DI SFRUTTAMENTO

La planimetria riportata a fianco evidenzia il passato di sfruttamento del comparto, che ha ospitato attività con significative ricadute ambientali e un elevato grado di inquinamento.
In particolare, si fa riferimento allo scarico abusivo di sostanze pericolose all'interno della depressione dell'ex cava, che nel tempo ha prodotto melme acide e contaminato i terreni circostanti.
L'elevata acidità di queste sostanze ha inoltre determinato la compromissione dei terreni di riporto utilizzati per la parziale copertura della depressione.
Altre porzioni del comparto sono state interessate dalla presenza di una discarica di rifiuti urbani, attiva negli anni '70 in epoca antecedente all'emanazione delle prime normative sulla gestione dei rifiuti e sulla regolamentazione delle discariche. La parte sud dell'ambito è stata sin dai primi anni '90 inserita nel Piano Cave della Provincia di Bergamo e oggetto di attività estrattive per la produzione di ghiaia e sabbia, successivamente oggetto di azioni di ripristino ambientale.
La porzione nord-occidentale del comparto è stata sede di un intervento di estrazione di materiali inerti destinati alla realizzazione delle infrastrutture viarie, in particolare per la costruzione della variante Bergamo-Zanica della S.P. 115. In tale ambito, il ripristino dei luoghi è stato effettuato attraverso il conferimento di terre e rocce da scavo. Si evidenzia infine la presenza sull'area di piste di rullaggio e di hangar a servizio dell'aeroporto militare di Orio al Serio attivo a partire dalla fine degli anni '30 le cui tracce sono ancora visibili attraverso le riprese aeree del 1954.

L'intervento attuale si configura quindi anche come un'importante opportunità di riqualificazione ambientale, capace di restituire valore e qualità a suoli compromessi e di rigenerare un contesto in grado di offrire nuove funzioni ecosistemiche e una rinnovata connessione tra ambiente naturale e tessuto urbano.

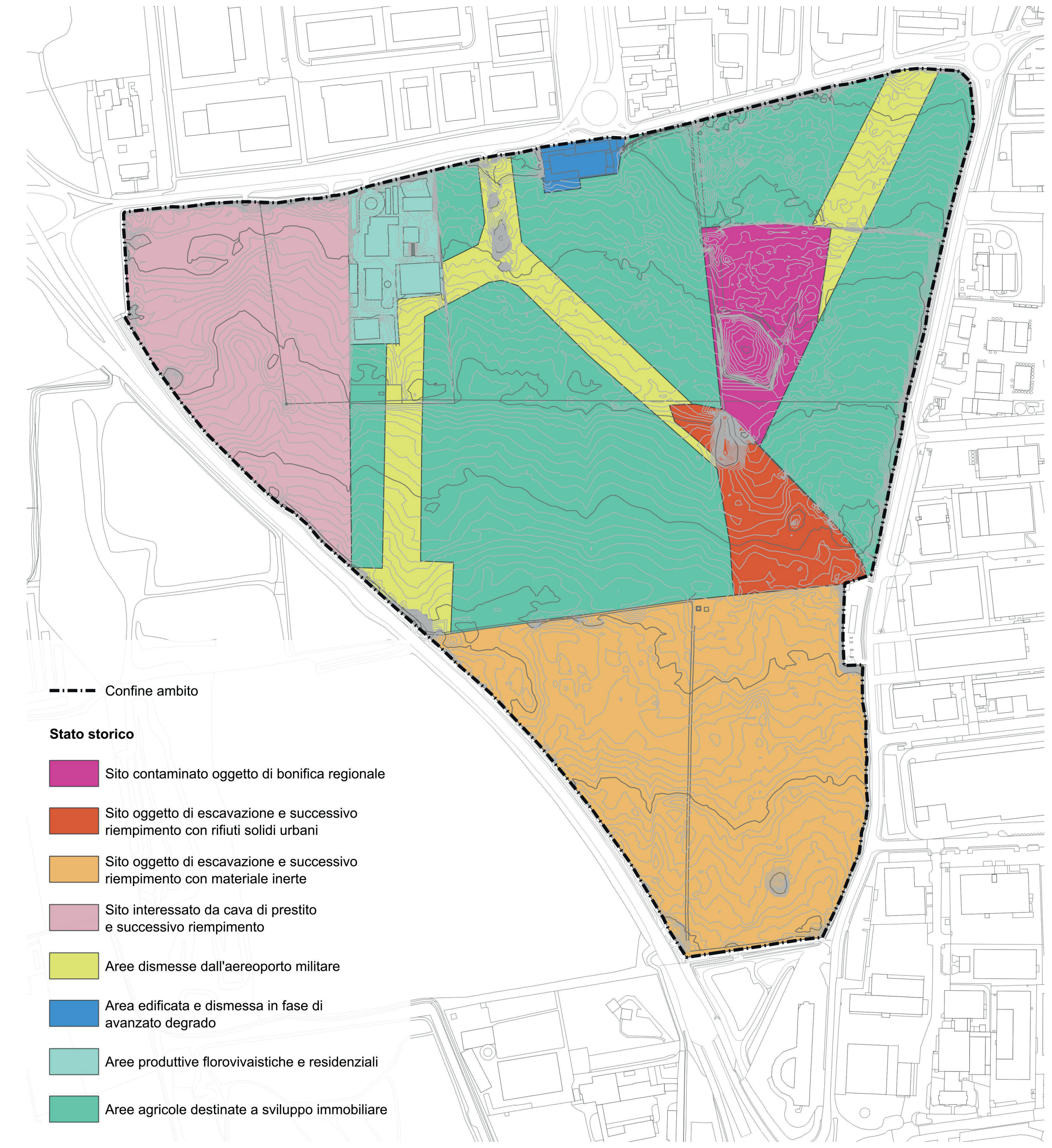
Confine ambito
Stato storico
Sito contaminato oggetto di bonifica regionale
Sito oggetto di escavazione e successivo riempimento con rifiuti solidi urbani
Sito oggetto di escavazione e successivo riempimento con materiale inerte
Sito interessato da cava di prestito e successivo riempimento
Aree dismesse dall'aereoporto militare
Area edificata e dismessa in fase di avanzato degrado
Aree produttive florovivaistiche e residenziali
Aree agricole destinate a sviluppo immobiliare

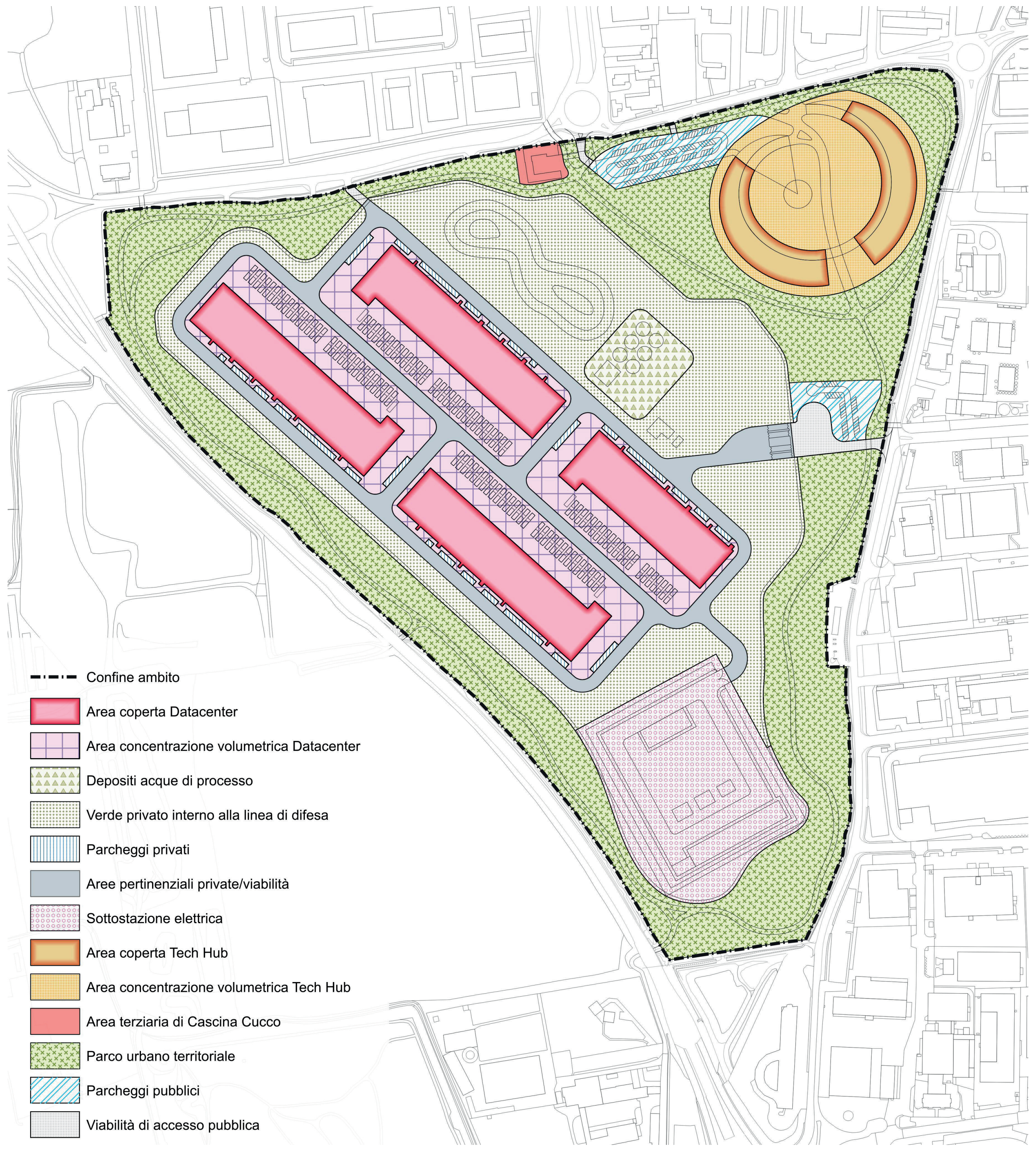
Confine ambito
Area coperta Datacenter
Area concentrazione volumetrica Datacenter
Depositi acque di processo
Verde privato interno alla linea di difesa
Parcheggi privati
Aree pertinenziali private/viabilità
Sottostazione elettrica
Area coperta Tech Hub
Area concentrazione volumetrica Tech Hub
Area terziaria di Cascina Cucco
Parco urbano territoriale
Parcheggi pubblici
Viabilità di accesso pubblica

DATI TERRITORIALI ALLA SOGLIA DEL PROGETTO

	(mq)	SOMMA (mq)	%
Aree Terziarie di Cascina Cucco	1.753	1.753	0,40%
Area Terziario direzionale con attività di ricerca e coworking	34.575	256.407	58,59%
Area Produttiva per attività computing e storage	95.263		
Aree private e pubbliche di servizio	126.569		
Verdi privati drenanti con valenza di mitigazione ambientale	46.734	179.477	41,01%
Aree pubbliche a valenza ecosistemica	132.743		
TOTALE AMBITO DI INTERVENTO	437.637	437.637	100,00%

UN TERRITORIO FERITO: NUOVE OPPORTUNITÀ DI RIGENERAZIONE

Il nuovo polo rappresenta un'opportunità unica per ripensare lo sviluppo del territorio di Zanica in una prospettiva più ampia e integrata.
Si tratta di un modello che va oltre la semplice infrastruttura tecnologica, diventando un punto di riferimento per il sistema della mobilità lenta, i servizi, la produttività e la sostenibilità ambientale.

Un Hub di Connessione tra Mobilità e Sviluppo Territoriale
L'ambito, grazie alla sua posizione strategica, dotata di un elevato profilo di accessibilità assicurato dalla presenza dell'Autostrada A4, della SP591 "Cremasca", della SP15 e dalla vicinanza con l'Aeroporto "il Caravaggio", si configura come un vero nodo intermodale, capace di mettere in relazione la mobilità internazionale con quella regionale e locale. Non si tratta più solo un luogo di transito, ma si trasforma in un motore economico e tecnologico, in grado di attrarre investimenti e rafforzare il ruolo di Zanica nel sistema territoriale bergamasco.
La presenza dell'aeroporto, unita alla vicinanza con un importante tessuto produttivo e commerciale di contesto, rafforza ulteriormente la vocazione economica di quest'area, rendendola un punto di attrazione per nuove attività produttive e terziarie. Il potenziale di sviluppo è significativo: oltre ad un polo ad elevato contenuto tecnologico, il progetto prefigura la presenza di spazi per attività direzionali e servizi avanzati, centri di ricerca e sviluppo.

Nuove Aree Ecosistemiche e di Fruizione Collettiva
Contestualmente, il progetto pone una forte enfasi sulla valorizzazione ambientale attraverso la creazione di aree ecosistemiche e spazi di fruizione collettiva per il benessere della comunità. Questi interventi che mirano a ristabilire un equilibrio ecologico, rafforzare la resilienza del territorio, mitigare il rischio idrogeologico, offrono anche nuove opportunità di socializzazione e benessere, contribuendo alla creazione di spazi pubblici inclusivi e accessibili tramite il rafforzamento della rete di mobilità dolce.

In questo scenario, la trasformazione territoriale non si limita a una semplice riqualificazione, ma si configura come un modello di sviluppo innovativo e integrato, in grado di coniugare crescita economica, benessere sociale e sostenibilità ambientale.

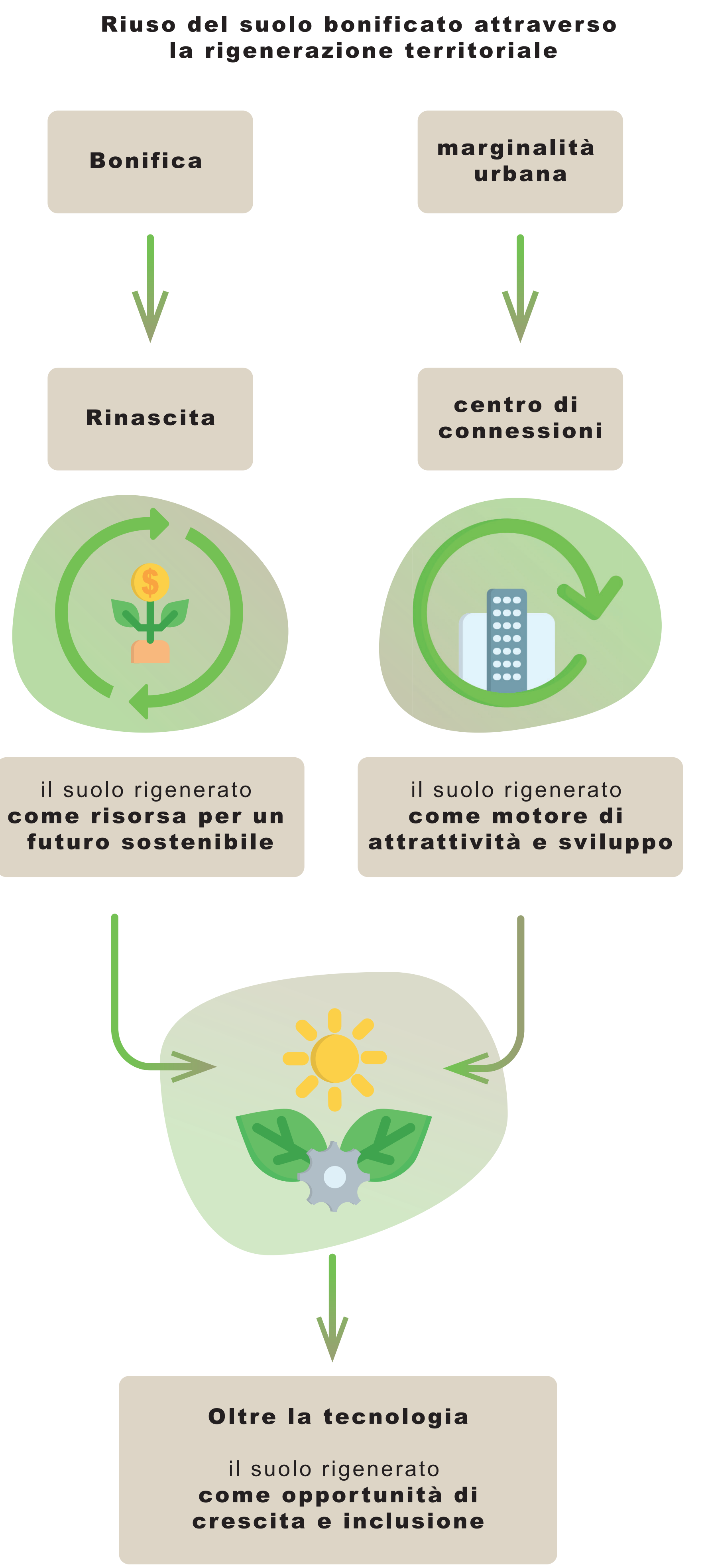

Riuso del suolo bonificato attraverso la rigenerazione territoriale

Bonifica

marginalità urbana

Rinascita

centro di connessioni

il suolo rigenerato **come risorsa per un futuro sostenibile**

il suolo rigenerato **come motore di attrattività e sviluppo**

Oltre la tecnologia

il suolo rigenerato **come opportunità di crescita e inclusione**

La rigenerazione territoriale del suolo bonificato deve abbracciare un **approccio inclusivo**, capace di integrare **sviluppo economico e sociale**. Questo significa promuovere **nuovi modelli di economia circolare**, potenziare i servizi alla comunità e valorizzare attività culturali e formative.

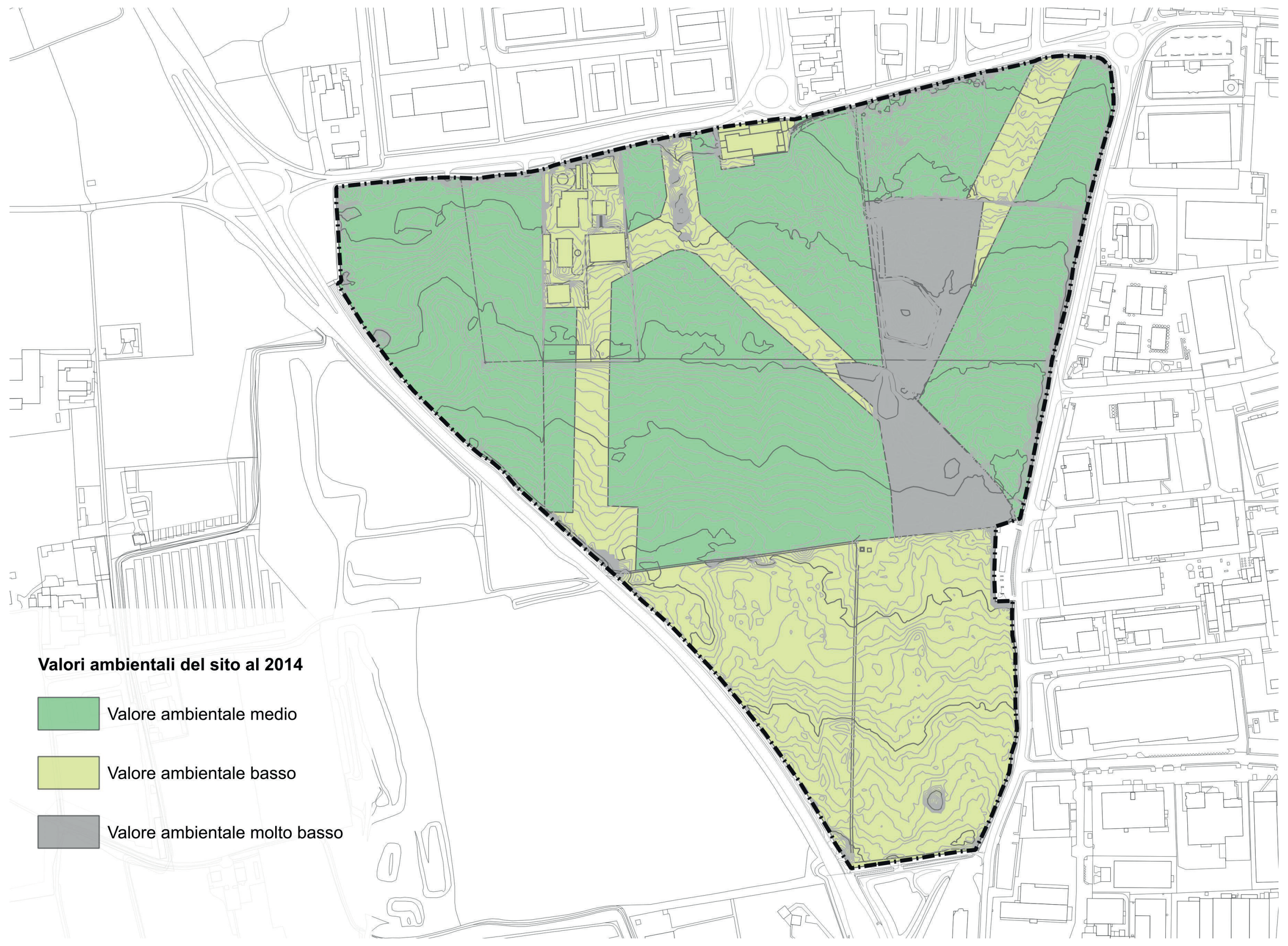
Valori ambientali del sito al 2014
Valore ambientale medio
Valore ambientale basso
Valore ambientale molto basso

INDIVIDUARE LE PECULIARITÀ DEL CONTESTO, RESTITUIRE VALORE E QUALITÀ AI SUOLI

La definizione dei valori ambientali delle aree interessate dall'intervento si fonda su un'analisi approfondita delle caratteristiche pedologiche, considerando le pregresse funzioni e le qualità intrinseche dei suoli. A questa valutazione si affianca un'indagine dettagliata dei valori paesaggistici, condotta a scala di dettaglio, al fine di definire un quadro complessivo della potenzialità ecosistemica e della qualità ambientale del sito.

Il confronto tra lo stato di fatto e la configurazione progettuale evidenzia un significativo incremento della qualità ambientale, reso possibile da azioni mirate di valorizzazione e riqualificazione dei suoli. L'intervento consente di individuare ampie superfici con elevati valori ambientali, particolarmente in relazione alla loro capacità di offrire servizi ecosistemici e spazi di fruizione naturalistica collettiva.

Attraverso un processo di rigenerazione del comparto, il progetto promuove una revisione critica del sistema preesistente, caratterizzato da un uso del suolo intensivo e ambientalmente poco attento. L'integrazione di strategie di recupero e valorizzazione paesistico-ambientale contribuisce, al contrario, a delineare un nuovo assetto territoriale, orientato alla sostenibilità e alla resilienza ecologica, in cui una ritrovata naturalità diviene elemento chiave per il miglioramento della qualità della vita collettiva e della biodiversità.

DATI TERRITORIALI - VALORI AMBIENTALI

AMBITO URBANISTICO	PGT VIGENTE (mq)	PROGETTO (mq)	Differenza (mq)
VALORE AMBIENTALE MOLTO ALTO		132.743	**132.743**
VALORE AMBIENTALE MEDIO	243.543	82.303	**-161.240**
VALORE AMBIENTALE BASSO	157.418	222.591	**65.173**
VALORE AMBIENTALE MOLTO BASSO	36.676		**-36.676**
TOTALE AMBITO DI INTERVENTO	437.637	437.637	0

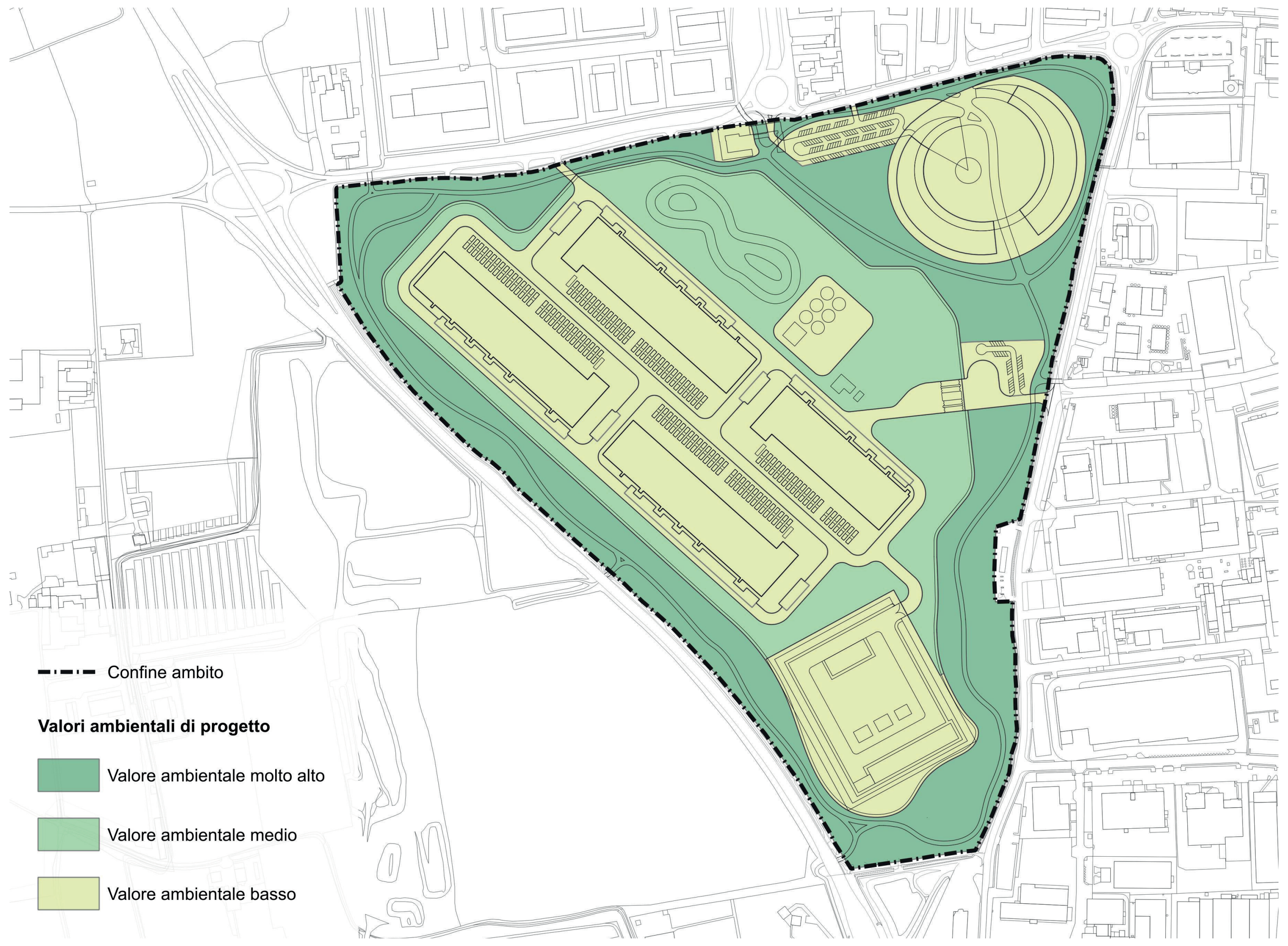
Confine ambito
Valori ambientali di progetto
Valore ambientale molto alto
Valore ambientale medio
Valore ambientale basso

ACCORDO DI PROGRAMMA

RIGENERAZIONE URBANA E TERRITORIALE DELL'AMBITO DI TRASFORMAZIONE AT1

NUOVO POLO TECNOLOGICO DI INTERESSE SOVRALOCALE

PROVINCIA DI BERGAMO
Via Torquato Tasso 8
24121 Bergamo
PEC protocollo@pec.provincia.bergamo.it
Tel 035387111

COMUNE DI ZANICA
Via Roma 35
24050 Zanica
PEC protocollo@pec.comune.zanica.bg.it
Tel 0354245811

PROMOTORE
Real Estate SPV Project 2415 S.r.l.
Corso Vittorio Emanuele II No. 24/28
20122 – Milano (Italia)
PEC realestatespvproject2415@legalmail.it
Tel +39 02 7788051 -

B - INDICAZIONI DI PIANO: POSTERPLAN DEI PRINCIPALI OBIETTIVI E DELLE AZIONI DI PROGETTO	SCALA	DATA SETTEMBRE 2026	
TITOLO TAVOLA CONTENIMENTO DEL CONSUMO DI SUOLO: MIGLIORAMENTO DEI PARAMETRI DI QUALITA' AMBIENTALE	NUMERO TAVOLA **B2**	AGGIORN. AGGIORN. AGGIORN.	N

TAVOLO TECNICO ISTITUZIONALE

COMUNE DI ZANICA:
UFFICIO URBANISTICA EDILIZIA PRIVATA E SUE
Dirigente
Dott. arch. Gianluca Della Mea
gianluca.dellamea@comune.zanica.bg.it
tel. 035 4245811 int 3

PROGETTISTI E CONSULENTI

PROGETTO URBANISTICO E COORDINAMENTO GENERALE
Marcello Fiorina - ingegnere
Elisabetta Nani - ingegnere
Studio associato di architettura urbanistica ed ingegneria
Sede in via pignolo 5, Bergamo tel 035-218094 - 035-270308
www.studiofiorina.com - indirizzo email: info@studiofiorina.com

PAESAGGIO AMBIENTE E NATURA
Studio Gerundo
Arch. Paolo Pelliccioli
Ing. Susanna Quirico
Dott. Agr. Alberto Massa Saluzzo
Via Cagnola 25 – Treviglio
Tel 3475331955 e-mail: info@studiogerundo.it

RKD
Kevin Maguire
Derek Meenan
The Eight Building
Dublin - Ireland - D08 T2TX
Tel +353 1 668 1055 e-mail: mail@rkd.ie
https://www.rkd.ie

BEAST Design Studios GmbH
Gustavo Espigado
Kölner Str. 1
Eschborn - Germany - 65760
Tel +49 (0) 6196 7700 410
e-mail: g.espigado@beastdesignstudios.com
www.beastdesignstudios.com

ENGINEERING AND INFRASTRUCTURE
ETS Engineering and Technical Services SpA
Donato Romano
Via Angelo Mazzi, 32
Villa d'Almè - Bergamo - 24018
Tel +39 035 6313111 e-mail: info@etseng.it
https://www.etseng.it/

TRASPORTI, AMBIENTE, INVARIANZA IDRAULICA
TE.A. CONSULTING SRL

VALUTAZIONE AMBIENTALE STRATEGICA
TE.A. CONSULTING SRL
ING. MASSIMO MOI
MI Via G.B. Grassi 15 - 20157 Milano (MI)
T 02 21711067
BG Via Don A. Mazzucotelli 6 - 24020 Gorle (BG)
T 035 321360
www.territorioambiente.com

H&MV Engineering
Paul O'Helleran, Fabio Sbacches
Hamilton House Block 2
Castletroy - Ireland - V94 YHD6
Tel +35 36 135 7496 e-mail: info@hmvengineering.com
https://www.hmvengineering.com/