C1 VERIFICA DI COERENZA CON LA PIANIFICAZIONE COMUNALE

L'AMBITO DI RIFERIMENTO PER LA PIANIFICAZIONE TERRITORIALE

L'area in oggetto, di ampia estensione territoriale, si configura come una zona di cerniera situata al margine settentrionale del territorio comunale di Zanica, assumendo un ruolo di transizione tra il tessuto urbano consolidato e gli ambiti produttivi adiacenti. Il perimetro dell'area è definito a ovest dalla Strada Provinciale 591 bis, infrastruttura viaria di rilevanza sovralocale che garantisce un'elevata accessibilità, mentre a est e a sud il contesto è caratterizzato dalla presenza di comparti produttivi appartenenti ai comuni limitrofi di Azzano San Paolo, Orio al Serio e Grassobbio, configurandosi come un nodo territoriale intercomunale ad alta connettività.

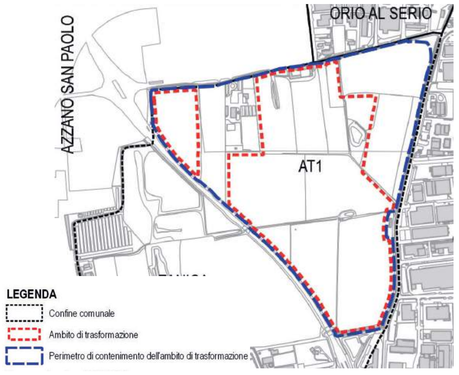
Per l'ambito il PGT definisce i seguenti

parametri urbanistico - edilizi di riferimento:

Perimetro di contenimento dell'AdT:	438.595mq
Superficie territoriale (ST):	318.595mq
Superficie Lorda (SL):	152.500mq
Indice di copertura (IC):	0,50mq/mq
Superficie Permeabile (SP):	95.579mq

Altezza: da valutarsi nell'ambito della proposta attuativa in relazione al corretto inserimento nel contesto paesaggistico e al rispetto delle mappe di vincolo aeroportuale

L'attuazione dell'intervento deve inoltre garantire il reperimento di aree libere per una superficie territoriale minima pari a 120.000mq finalizzato alla riduzione del consumo di suolo



OBIETTIVI PER L'AMBITO DI TRASFORMAZIONE "AT1 - POTENZIAMENTO E RIORDINO DEGLI INSEDIAMENTI PRODUTTIVI"

Obiettivi Generali di PGT

- 03a Declinare temi e principi strategici dell'agenda ONU 2030
- 03b Costruire una rete ecologica intercomunale (PTCP)
- 03f Progettare barriere e filtri verdi di interposizione tra insediamenti produttivi e zone residenziali.
- 04c Mobilità attiva pedonale e ciclabile: quadro di riferimento Rete della mobilità attiva intercomunale (PTCP); valorizzare le dorsali degli itinerari ricreativi.
- 06a Sostenere una nuova generazione di attività produttive: non depauperare anzi potenziare il sistema produttivo locale, orientandolo ad una sempre migliore compatibilità ambientale e verso forme di produzione innovativa ad alto contenuto tecnologico (Distretto Green).
- 06b Perseguire una migliore compatibilità ambientale degli insediamenti produttivi: in termini generali (riduzione degli impatti sulle matrici ambientali); in termini specifici (compatibilità con ambiti di contatto residenziali).
- 06c Introdurre, anche a livello normativo, concetti di 'impronta' ecologica e sostenibilità dei cicli produttivi, criteri di 'performance' ambientale e governo delle ricadute sul territorio: compensazione (sostenibilità e resilienza urbana, riduzione impatto climatico ed effetto «isola di calore», minimizzazione delle emissioni, permeabilizzazione delle superfici, compensazione e produzione di servizi ecosistemici, ecc.).
- 06d Qualificare l'offerta di spazi e funzioni integrative a servizio del sistema produttivo
- 06e Compensazioni ambientali/ecologiche
- 06f Attivazione di forme di comunità energetiche rinnovabili
- 06g Governance condivisa della mobilità

Obiettivi Specifici

- Attivare una nuova polarità urbana di attrattività e rilevanza sovracomunale.
- Prevedere funzioni miste e integrate di carattere terziario e produttivo avanzate, innovative e ad alto contenuto tecnologico

Ulteriori obiettivi

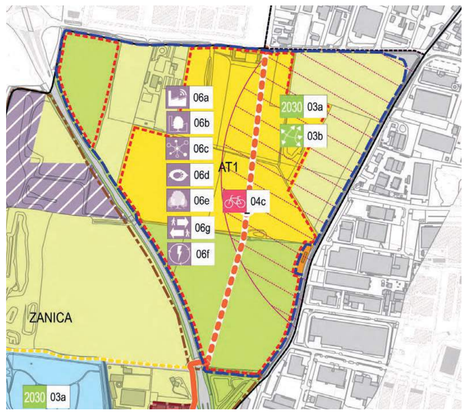
La trasformazione dell'area avrà come requisito imprescindibile la verifica della qualità dei suoli. Dovranno essere applicati i parametri ecologici con particolare attenzione alla forestazione urbana utilizzando specie arboree con elevata capacità filtrante dell'aria. Dovranno essere previste e realizzate opere di compensazione ambientale per invarianza idraulica (laminazione/drenaggio profondo), anche mediante programmi di verifica ed eventuali interventi che assicurino il regolare deflusso delle reti drenate naturali e/o antropiche. Acquisizione da parte del Comune di Zanica a titolo compensativo del 10% della ST, finalizzato alla delocalizzazione di attività produttive ad oggi presenti nel centro abitato e all'inserimento di un incubatore per start up innovative.
L'intervento dovrà contribuire alla realizzazione della dorsale ciclopedonale "Via Padergnone - Aeroporto".
È escluso l'insediamento di nuove ditte a rischio di incidente rilevante ai sensi del D.lgs. 105/2015.

Criteri insediativi e di qualità urbana

L'intervento dovrà assicurare la piena valorizzazione del rapporto tra nuovi insediamenti e contesto paesaggistico rurale, anche attraverso uno specifico studio paesaggistico di dettaglio.
L'intervento dovrà prevedere filtri o barriere vegetazionali d'interposizione tra insediamenti produttivi e spazi aperti/ambiti agricoli o forestali.

Procedure di risanamento ambientale - bonifiche

Gli interventi di trasformazione dovranno essere preceduti da indagini geotecniche specifiche in corrispondenza dei settori oggetti di riporto.
Gli interventi non dovranno comunque alterare i presidi ambientali connessi alla bonifica e alla discarica di inerti. Dovranno essere evitate infiltrazioni di acque meteoriche che interferiscano con le aree manomesse.
Gli interventi nell'ambito dovranno assumere come riferimento le migliori pratiche relative al drenaggio urbano sostenibile.
L'attuazione dell'ambito dovrà essere assoggettata a specifica Valutazione di Impatto Ambientale e/o Valutazione Ambientale Strategica, da espletarsi nelle modalità coerenti con la normativa vigente in materia.
L'ambito è assoggettato alla definizione di una Intesa Strategica ai sensi del titolo 15 delle Regole di Piano del PTCP vigente.



Sito bonificato soggetto a onere reale ai fini della bonifica

L'AT1 ricomprende un sito oggetto di intervento di bonifica d'ufficio e pertanto le aree afferenti la proprietà del sito sono gravate dall'onere reale di cui all'art. 253 del d.lgs. n. 152/2006, stimato in € 5.398.000,00.
Gli interventi di bonifica costituiscono onere reale sui fondi contaminati in quanto effettuati d'ufficio dall'autorità competente ai sensi dell'articolo 250 del Dlgs 152/2006.
Le spese sostenute per tali interventi, sono assistite da privilegio speciale immobiliare sulle aree medesime, ai sensi e per gli effetti dell'articolo 2748, secondo comma, del codice civile. Detto privilegio si può esercitare anche in pregiudizio dei diritti acquistati da terzi sull'immobile.

GLI OBIETTIVI CONDIVISI STABILITI ATTRAVERSO UN PROTOCOLLO DI INTESA

Nell'ottica di promuovere e attuare congiuntamente un Accordo di Programma per lo sviluppo urbanistico delle aree incluse nel comparto "AT1", l'Amministrazione Comunale e il soggetto attuatore dell'intervento di riqualificazione territoriale hanno sottoscritto un protocollo di intesa. Questo accordo getta le basi per un modello di sviluppo sostenibile e inclusivo, che coniuga la realizzazione di un polo tecnologico con un piano integrato di risanamento e compensazione ambientale di siti precedentemente contaminati.
L'iniziativa non solo rafforza l'economia locale e regionale, ma contribuisce anche a migliorare il benessere della comunità e la qualità ambientale nel lungo periodo. In particolare, i sottoscrittori hanno convenuto che il progetto di recupero e valorizzazione del comparto AT1

- può definire un modello di sviluppo sostenibile e inclusivo, che mostra come tecnologia e natura possano coesistere armoniosamente
- può garantire nuova occupazione in un settore ad alto tasso di innovazione, a basso impatto ambientale e senza rischio per la salute dei lavoratori;
- può generare un ulteriore forte indotto economico sul territorio di qualità e in grado di connettersi con le reti lunghe del sistema aeroportuale e dalla ricerca provinciale e regionale;
- si pone come ulteriore occasione di sostegno anche al rilancio del sistema economico e produttivo locale;
- è in grado di attuare le politiche ambientali e di risanamento definitivo del compendio su cui andrà ad insistere;
- può garantire, tutelare e riconoscere al Comune ogni ristoro e risarcimento funzionali a bilanciare gli interventi di risanamento e bonifica attuati direttamente dal soggetto pubblico su parte del compendio



UNA PROGETTUALITA' CONDIVISA

Di seguito sono individuati gli elementi qualificanti del progetto che rappresentano la traduzione operativa degli obiettivi strategici, gli obiettivi specifici e le prescrizioni del PGT e ne sviluppano i contenuti in termini progettuali, definendo le principali azioni attraverso cui l'intervento contribuisce alla qualificazione ambientale, funzionale e territoriale dell'ambito.

A - Attuazione della rete ecologica comunale: Declinazione operativa della rete ecologica comunale attraverso la realizzazione di sistemi di verde pubblico fruibile e verde privato di tutela, finalizzati alla ricostituzione della naturalità (Rif. obiettivi PGT 03b – 03f)

B - Potenziamento della mobilità attiva: Realizzazione di una rete di percorsi ciclopedonali integrata con il sistema della mobilità attiva intercomunale; in particolare è prevista il potenziamento della dorsale ciclopedonale "Via Padergnone – Aeroporto", fruibile sia come infrastruttura di spostamento quotidiano sia come itinerario ricreativo e paesaggistico, contribuendo a una gestione coordinata e sostenibile della mobilità locale.(Rif. obiettivi PGT 04c – 06g, ulteriori obiettivi)

C - Sviluppo di una polarità produttiva innovativa: Realizzazione di una polarità produttiva di nuova generazione, orientata allo sviluppo di attività di computing e storage ad elevato contenuto tecnologico, capace di rafforzare il sistema economico locale e contribuire alla formazione di un Distretto Green caratterizzato da elevata compatibilità ambientale.(Rif. obiettivi PGT 06a – 06b)

D - Sistemi insediativi a elevata performance ambientale: Introduzione di soluzioni progettuali a bassa impronta ecologica e ad alta performance ambientale, con particolare attenzione alla gestione sostenibile dei cicli delle risorse, alla permeabilizzazione delle superfici, alla riduzione dell'isola di calore e alla gestione integrata delle acque meteoriche.(Rif. obiettivi PGT 06c – 06e, ulteriori obiettivi)

E - Compensazioni ambientali ed ecologiche: Attivazione di sistemi di compensazione ambientale ed ecologica finalizzati alla produzione di servizi ecosistemici, al miglioramento della qualità paesaggistica e alla mitigazione degli impatti generati dalle trasformazioni insediative.(Rif. obiettivi PGT 06e, ulteriori obiettivi)

F – Nuova polarità urbana di rilevanza sovracomunale: Realizzazione di una nuova polarità urbana attrattiva, in grado di assumere un ruolo di riferimento per il territorio sovracomunale mediante l'integrazione di servizi, spazi pubblici e funzioni a supporto del sistema produttivo e della comunità locale. Il progetto, così come concepito assolve inoltre all'obiettivo di creare un Tech Hub, finalizzato alla realizzazione di un incubatore per start-up innovative oltre a favorire la delocalizzazione delle attività produttive attualmente insediate nel centro abitato. In tale prospettiva, l'Amministrazione ha ritenuto che l'individuazione del nuovo Tech Hub rappresenti non soltanto un intervento di riassetto e qualificazione territoriale, ma anche la proposta di un nuovo modello di spazi destinati alla produzione, fondato sull'integrazione tra attività economiche, innovazione, servizi, ricerca e qualità urbana. (Rif. obiettivo specifico 1 – obiettivo PGT 06d, ulteriori obiettivi)

G – Mix funzionale e integrazione tra produzione, ricerca e spazi collettivi: Introduzione di funzioni miste e integrate che combinano attività produttive avanzate, ricerca e innovazione, servizi e spazi pubblici di fruizione collettiva, favorendo l'interazione tra sistema economico, conoscenza e comunità locale; in tale quadro l'intervento intende inoltre ricollegare e valorizzare la rete ciclabile fruitiva storica, recuperando e integrando strade poderali e percorsi rurali esistenti.(Rif. obiettivo specifico 2)

Anche gli obiettivi delineati nel Protocollo di Intesa, trovano concreta attuazione nel progetto, che rappresenta l'esito di un articolato percorso di approfondimento e confronto sviluppato nell'arco di oltre un anno attraverso un tavolo tecnico appositamente costituito, che ha visto la partecipazione coordinata dei rappresentanti della parte pubblica e del soggetto attuatore, consentendo di definire progressivamente soluzioni progettuali condivise. In questo quadro condiviso, il progetto del comparto AT1:

- promuove un modello di sviluppo sostenibile e innovativo, in grado di integrare tecnologia, qualità ambientale e valorizzazione territoriale;
- genera nuova occupazione qualificata e rafforza il sistema economico e produttivo locale, con ricadute positive sull'indotto territoriale.
- garantisce adeguate forme di ristoro e compensazione a favore dell'ente pubblico, anche in relazione agli interventi di bonifica e risanamento già sostenuti.

LA MATRICE STRUTTURALE DEL PROGETTO

Il progetto riorganizza il comparto distinguendo in modo netto le superfici insediative da quelle a funzione ambientale. Dei complessivi 437.637 mq, 258.160 mq, pari al 58,98%, risultano urbanizzati o urbanizzabili, mentre 179.477 mq, pari al 41,02%, rimangono sostanzialmente liberi e destinati a verde drenante, aree ecosistemiche, agricole e fruitive.
La rilevanza della proposta non risiede soltanto nel mantenimento di circa metà dell'ambito non edificata, ma nell'equilibrio tra componente insediativa e componente ambientale. Il verde non assume quindi carattere residuale o ornamentale, ma costituisce una parte strutturale dell'impianto urbanistico, attraverso il Parco urbano territoriale, le fasce di mitigazione, le connessioni ecologiche e gli spazi di compensazione.
La tesi di fondo è che il suolo bonificato e rigenerato debba divenire un'infrastruttura territoriale, e non un semplice supporto edificatorio. La bonifica non è pertanto considerata una fase preliminare e separata dalla trasformazione, ma una componente essenziale del progetto, chiamata a produrre un miglioramento ambientale concreto mediante la restituzione di superfici alla naturalità, l'incremento delle dotazioni verdi, il rafforzamento della continuità ecologica e la creazione di nuovi spazi di fruizione collettiva. L'intervento supera così il modello della tradizionale area produttiva monofunzionale e configura una trasformazione capace di coniugare la realizzazione di una nuova polarità produttiva e tecnologica con la riqualificazione di un suolo segnato da usi impropri e condizioni di degrado.

I NUMERI DEL PROGETTO

179.477 mq di riduzione del consumo di suolo

132.743 mq destinati a nuovo parco pubblico urbano con valenza ecosistemica

82.303 mq di aree private di verde profondo di mitigazione ambientale

4.200 m di percorsi ciclopedonali per mobilità quotidiana e fruizione ricreativa

134.518 mq per un hub multifunzionale integrato come nuovo modello di sviluppo territoriale



RIQUALIFICAZIONE AREE ACCORDO DI PROGRAMMA

ZONA URBANISTICA	(mq)	SC (mq)	SL (mq)	permeabile	altezza
LOTTO 1- DATACENTER					
Area edificabile Datacenter (1A-1B-1C-1D)	95.263	46.509	93.018	no	25 m
Parcheggi privati (P1- P8)	9.592			semi	
Aree verdi private (VP1-VP2-VP3)	82.303			si	
Area depositi esterni acqua di processo (SA)	7.080			semi	
Viabilità privata interna (S1)	27.494			no	
Stazione Terna (T)	34.188			semi	
Totale lotto 1 -SF-	**255.920**	**46.509**	**93.018**		
LOTTO 2A - TECH HUB					
Area edificabile Tech hub (2A)	34.575	11.400	40.000	no	18 m
Totale lotto 2A -SF-	**34.575**	**11.400**	**40.000**		
LOTTO 2B - CASCINA CUCCO					
Edificio cascina Cucco (2B)	1.753	750	1.500	no	esist
Totale lotto 2B -SF-	**1.753**	**750**	**1.500**		
AREE PUBBLICHE					
Parco urbano territoriale (PU1-PU2-PU3)	132.743			si	
Parcheggio pubblico in superficie (PP1-PP2)	9.696			no	
Viabilità di accesso pubblica (SP1-SP2-SP3-SP4)	2.950			no	
Totale aree pubbliche o asservite uso pubblico	**145.389**				
TOTALE SUPERFICIE GENERALE - ST -	**437.637**	**58.659**	**134.518**		
PREVISIONE PGT VIGENTE	**438.595**	**-**	**152.500**		

VERIFICA DOTAZIONE SUPERFICIE PERMEABILE	ST (mq)				Permeabile
		Permeabile da regolamento edilizio			
Superficie territoriale generale dell'intervento	437.637	15%	65.646		
		Permeabile da PGT			Garantita
Superficie territoriale generale dell'intervento	437.637	30%	**131.291**	<	**215.046**
Aree verdi private (VP1-VP2-VP3)					82.303
Parco urbano territoriale (PU1-PU2-PU3)					132.743
Totale aree permeabili garantite					**215.046**
Totale aree permeabili garantite in % sulla ST			**30,0%**	<	**49,1%**

VERIFICA DOTAZIONE COMPLESSIVA STANDARD URBANISTICI		Dotazione pubblica attesa	
	mq	%	mq.
Superficie lorda produttiva	93.018	20% SL	18.604
Superficie lorda terziario direzionale ricettiva commerciale	40.000	100% SL	40.000
Superficie lorda terziario direzionale ricettiva commerciale Cascina Cucco	1.500	100% SL	1.500
Dotazione aggiuntiva piste ciclabili (su tutta la SL)	134.518	9mq/50mqSL	24.213
Totale			**84.317**
di cui a parcheggio			30.052
di cui a parco urbano			30.052
di cui al servizio ciclabile			24.213
		Dotazione pubblica garantita	
			mq.
Parco urbano territoriale (PU1-PU2-PU3) comprensivo di 24.213 mq di aree al servizio delle piste ciclabili			132.743
Parcheggio pubblico in superficie (PP1-PP2)			9.696
Totale			**142.439**

VERIFICA DI COERENZA CON LE PREVISIONI DI PGT

ELEMENTI DIMENSIONALI

La pianificazione attuativa proposta per lo sviluppo urbanistico-territoriale dell'ambito AT1 interessa un comparto con superficie territoriale complessiva pari a 437.637 mq. che, al netto di minime differenze dovute alla diversa scala di calcolo tra PGT e pianificazione di dettaglio, coincide con l'intero perimetro individuato dal PGT per l'AdT. Ricoprire l'ambito nella sua interezza significa governare la trasformazione in modo unitario: un unico disegno, un'unica regia, senza discontinuità tra parti e senza soluzioni episodiche. Questa scelta permette di coordinare fin dall'inizio assetto insediativo, opere di urbanizzazione e sistema degli spazi aperti, garantendo che ogni intervento concorra a un risultato complessivo coerente. In tal modo si dà piena attuazione agli obiettivi del PGT, evitando frammentazioni attuative e assicurando che infrastrutture, dotazioni ambientali e connessioni funzionali siano dimensionate e integrate sull'intero comparto. L'efficacia delle scelte progettuali ne risulta rafforzata, perché il progetto opera come trasformazione organica e non come somma di interventi parziali.
La scheda di Piano individua per l'ambito una SL massima pari a 152.000 mq. Il progetto assume tale riferimento come cornice di coerenza, prevedendo la realizzazione di 93.018 mq destinati alle funzioni produttive ad elevato contenuto tecnologico ed innovativo, a cui si affiancano 40.000 mq di superficie destinata alla realizzazione di un "Tech Hub", concepito come componente qualificante del nuovo polo tecnologico che potrà accogliere, oltre a funzioni direzionali e di servizio, anche attività di formazione e ricerca nel campo scientifico e tecnologico, rafforzando l'attrattività dell'insediamento e le sinergie con le principali polarità territoriali.
Il progetto risponde in modo pieno anche alla richiesta di 120.000 mq di aree libere finalizzate al contenimento del consumo di suolo. È infatti prevista la realizzazione di un parco urbano di oltre 132.000 mq, che costituisce la principale infrastruttura verde del comparto, cui si aggiungono aree verdi private per 82.303 mq. Nel loro insieme, tali superfici concorrono a strutturare un sistema continuo di spazi aperti e servizi ecosistemici, rendendo la trasformazione leggibile come intervento di rigenerazione e di incremento della qualità ambientale complessiva.
Nelle tabelle riportate a fianco sono sintetizzati i principali indicatori dimensionali, utili a verificare la coerenza quantitativa della proposta rispetto alle aspettative e ai parametri della pianificazione generale.

RETE ECOLOGICA COMUNALE

Nel Documento di Piano (stralcio cartografico riportato a fianco) la rete ecologica ha funzione strategica: traccia il disegno generale e orienta le trasformazioni con criteri ecologici e paesistici.
Nel contesto in esame non emergono elementi puntuali di particolare rilievo; proprio per questo il progetto dovrà assumere un ruolo attivo, costruendo una previsione attuativa capace di rafforzare ed estendere le connessioni ecologiche ed ecotonali fino al margine con il sistema produttivo del quadrante nord-est.

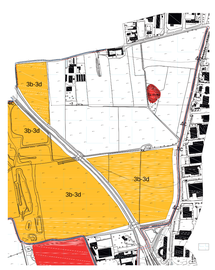


La rete ecologica del Piano dei Servizi opera invece in chiave attuativa: traduce gli indirizzi in una rete più definita e "progettuale", costruita come sistema di spazi aperti fruibili (parchi, fasce verdi, percorsi) e di connessioni ecologiche alla scala urbana. In questa logica, il verde non è solo dotazione, ma infrastruttura ambientale capace di ricucire margini, migliorare continuità ecologica e supportare funzioni di drenaggio e microclima.
Per l'ambito in esame, la pianificazione attuativa dovrà valorizzare i verdi privati e pertinenziali di tutela come componenti della continuità ambientale, integrandoli con infrastrutture verdi e blu e con nuovi servizi ecosistemici che qualificano l'intervento e ne amplificano le sinergie territoriali.



COMPONENTE GEOLOGICA DI PIANO

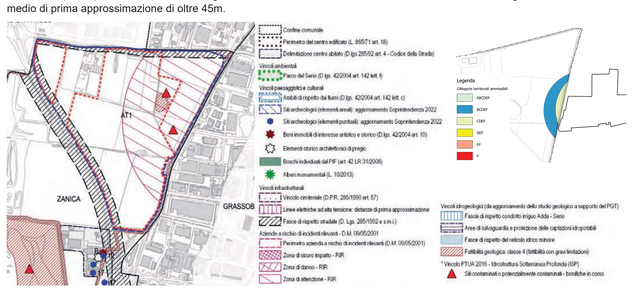
Nel rilevare un evidente errore materiale, per cui la disciplina di riferimento per l'area deve essere quella relativa alle zone 3c e non 3b (quest'ultima riferita ad aree comprese tra i limiti delle fasce B e C del PAI), la tavola della fattibilità geologica di Piano individua, per una parte dell'area interessata dal progetto, limitazioni di carattere geotecnico che richiedono specifici approfondimenti di indagine, da eseguire in conformità alle Norme Tecniche per le Costruzioni, in ragione delle pregresse attività di escavazione e riempimento.
La restante porzione, invece, non presenta elementi di significativa criticità ed è pertanto classificata come Classe 1 – Fattibilità senza particolari limitazioni.
Per la sola area interessata dallo scarico di melme inquinanti è stata individuata la classe 4, con possibilità di riclassificazione in una classe inferiore a seguito dell'avvenuta bonifica. Il progetto in ogni caso non prevede per quest'area alcun intervento di edificazione. Il progetto conformandosi alle indicazioni, prevede che la fase esecutiva sia preceduta da un'adeguata campagna di indagini geognostiche, geotecniche e geofisiche, comprendente sondaggi meccanici, prove penetrometriche e prove geofisiche. Tali attività consentiranno di definire le caratteristiche meccaniche dei terreni, gli spessori e la stratigrafia del sottosuolo, di individuare con precisione la quota del terreno naturale sottostante e di determinare i parametri sismici di riferimento.



Gli esiti delle indagini costituiranno parte integrante dello sviluppo progettuale e guideranno la definizione delle soluzioni tecniche più appropriate, con particolare riferimento alla scelta e al dimensionamento delle fondazioni. In questo modo, il progetto recepisce le prescrizioni derivanti dalla valutazione geologica e garantisce l'adozione di soluzioni idonee ad assicurare la stabilità e la sicurezza delle costruzioni. Il progetto rispetta infine il vincolo relativo alla fascia di rispetto del reticolo irriguo consortile, mantenendo la prescritta distanza dall'argine.

VINCOLI AMBIENTALI, PAESAGGISTICI E CULTURALI, INFRASTRUTTURALI, IDROGEOLOGICI

Come evidenziato dalla cartografia riportata, l'ambito AT1 non risulta interessato da vincoli paesaggistici ai sensi del D.Lgs. 42/2004, né da vincoli di natura forestale.
Sono invece presenti fasce di rispetto di natura infrastrutturale, connesse alla rete viaria di contesto. In particolare, lungo la SS 591 bis (strada di categoria C – extraurbana secondaria) il Regolamento di attuazione del Codice della Strada (D.P.R. 495/1992) prevede una fascia di rispetto pari a 30 m. Per la S.P. 115, che corre sul lato settentrionale del comparto, la fascia di rispetto è invece pari a 20 m, in ragione della classificazione come strada di tipo F – locale.
In relazione al vincolo ambientale derivante dalla presenza, sul territorio comunale di Grassobbio dell'azienda RIR "ERCA spa", si evidenzia che a seguito dell'aggiornamento dell'ERIR approvato dal comune di Zanica (vedi stralcio cartografico riportato), si rileva la coerenza delle funzioni previste dal progetto con le limitazioni derivanti dalla presenza di situazioni di potenziale rischio
Si evidenzia inoltre che l'ambito è interessato dalla presenza di vincolo aeroportuale e, in particolare, dalla superficie orizzontale interna che pone quale limite altimetrico degli edifici l'altezza di 274,95m s.l.m., altezza che consente, in ogni caso, un franco libero medio di prima approssimazione di oltre 45m.



VINCOLI AMBIENTALI, PAESAGGISTICI E CULTURALI, INFRASTRUTTURALI, IDROGEOLOGICI

Sottoilprofilo archeologico, l'areainteressata dalprogetto è caratterizzata prevalentemente da un potenziale archeologico generico, al quale non è associato, allo stato attuale delle conoscenze, un livello di rilevanza archeologica significativo.
Tale classificazione non evidenzia la presenza accertata di beni archeologici nel sedime di intervento, ma segnala la possibilità astratta di rinvenimenti, propria di un contesto territoriale storicamente antropizzato.



Un livello di attenzione maggiore interessa le aree poste in prossimità del tracciato storico di via Padergnone, classificate a potenziale archeologico alto.
Il quadro conoscitivo evidenzia, in particolare, la presenza della cascina storica "Cucco" e di segni riconducibili alla centuriazione, che documentano la stratificazione storica e l'antica organizzazione agraria del territorio.
La disciplina vigente stabilisce che, negli ambiti classificati alla lettera a) come "Aree a potenziale archeologico alto", i progetti relativi a interventi che comportino scavi, anche di minima entità, o qualsiasi forma di manomissione del sottosuolo siano trasmessi alla Soprintendenza competente ai fini dell'espressione del relativo parere. Negli ambiti classificati alla lettera b) come "Aree a potenziale archeologico generico", la trasmissione alla Soprintendenza è invece prevista per i progetti riguardanti le maggiori trasformazioni territoriali.
Nel complesso, il quadro archeologico non determina condizioni ostative alla realizzazione dell'intervento. La compatibilità del progetto è assicurata dal rispetto delle procedure di verifica e di valutazione preventiva previste dalla disciplina vigente, con particolare attenzione alle aree prossime al tracciato storico di via Padergnone.

ACCORDO DI PROGRAMMA

RIGENERAZIONE URBANA E TERRITORIALE DELL'AMBITO DI TRASFORMAZIONE AT1

NUOVO POLO TECNOLOGICO DI INTERESSE SOVRALOCALE



PROVINCIA DI BERGAMO
Via Torquato Tasso 8
24121 Bergamo
PEC protocollo@pec.provincia.bergamo.it
Tel 035387111

COMUNE DI ZANICA
Via Roma 35
24050 Zanica
PEC protocollo@pec.comune.zanica.bg.it
Tel 0354245811

PROMOTORE
Real Estate SPV Project 2415 S.r.l.
Corso Vittorio Emanuele II No. 24/28
20122 – Milano (Italia)
PEC realestatespvproject2415@legalmail.it
Tel +39 02 7788051 -

C - PIANIFICAZIONE URBANISTICA	SCALA	DATA
		SETTEMBRE 2026

TITOLO TAVOLA	NUMERO TAVOLA	AGGIORN.
VERIFICA DI COERENZA CON LA PIANIFICAZIONE COMUNALE	C1	AGGIORN.
		AGGIORN.

N

TAVOLO TECNICO ISTITUZIONALE

COMUNE DI ZANICA:
UFFICIO URBANISTICA EDILIZIA PRIVATA E SUE
Dirigente
Dott. arch. Gianluca Della Mea
gianluca.dellamea@comune.zanica.bg.it
tel. 035 4248811 int 3

PROGETTISTI E CONSULENTI

PROGETTO URBANISTICO E COORDINAMENTO GENERALE
Marcello Fiorina - ingegnere
Elisabetta Nani - ingegnere
Studio associato di architettura urbanistica ed ingegneria
Sede in via pignolo 5, Bergamo tel 035-218094 - 035-270308
www.studiofiorina.com - indirizzo email: info@studiofiorina.com

PAESAGGIO AMBIENTE E NATURA
Studio Gerundo
Arch. Paolo Pellicciotti
Ing. Susanna Quirico
Dott. Agr. Alberto Massa Saluzzo
Via Cagnola 26 – Treviglio
tel 3473331955 e-mail: info@studiogerundo.it

RKD
Kevin Maguire
Derek Meeman
The Eight Building
Dublin - Ireland - D08 T2TX
Tel +353 1 668 1055 e-mail: mail@rkd.ie
https://www.rkd.ie

BEAST Design Studios GmbH
Gustavo Espigado
Kaiserstr. 39
60329 Frankfurt - Germany – 60760
Tel +49 (0) 69 86 7750 410
e-mail: g.espigado@beastdesignstudios.com
www.beastdesignstudios.com

ETS Engineering and Technical Services SpA
Donato Romano
Via Angelo Mazzi, 32
BG Via Don A. Mazzucconelli 6 - 24016
Tel +39 035 4313111 e-mail: info@etseng.it
https://www.etseng.it

TRASPORTI, AMBIENTE, INVARIANZA IDRAULICA
TE.A. CONSULTING SRL
ING. MASSIMO MOI
MI Via G.B. Grassi 15 - 20157 Milano (MI)
T 02 27171067
BG Via Don A. Mazzucconelli 6 - 24020 Gorle (BG)
T 035 321360
www.territorioambiente.com

VALUTAZIONE AMBIENTALE STRATEGICA
TE.A. CONSULTING SRL
ING. MASSIMO MOI
MI Via G.B. Grassi 15 - 20157 Milano (MI)
T 02 27171067
BG Via Don A. Mazzucconelli 6 - 24020 Gorle (BG)
T 035 321360
www.territorioambiente.com

H&MV Engineering
Paul O'Helleran, Fabio Sbaches
Hamilton House Stockley Park
Uxbridge, Middlesex, UB11 1AY, UK
Tel +35 36 132 7456 e-mail: info@hmvengineering.com
https://www.hmvengineering.com/